Sperr- und Gefahrenzonenkarte – Carte des zones interdites

Zeichenerklärung – Signes conventionnels

TRAININGSRÄUME
SECTEURS D'ENTRAÎNEMENT FL 100/130 – 660 (inkl.)

Ausnahmen, bezeichnet mit:
Exceptions, avec le signe:

① FL 130 – 160
② North of line FL 130/210 – 660 (according to ADDC)
③ FL 130 – 240
④ FL 130 – 180
⑤ FL 100 – 180
⑥ EUC25FE/FC: FL 115 – FL 195
⑦ EUC25FW: FL 065 – FL 195
⑧ LFR158A: 5000 AGL – FL 115
LFR158B: 1500 AGL – 5000 AGL
⑨ EUC60 CH: FL 130 – FL 280 / I: FL 200 – FL 280
EUC660 CH: FL 130 – FL 660 / I: FL 200 – FL 660
⑩ EUC25SL: FL 100 – FL 230
EUC25SLP: FL 100 – FL 230
EUC25SH: FL 250 – FL 660
⑪ FL 130 – FL 280

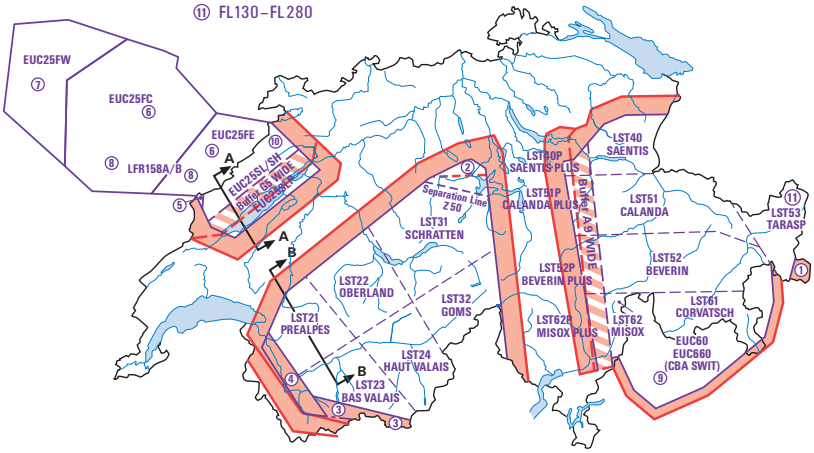

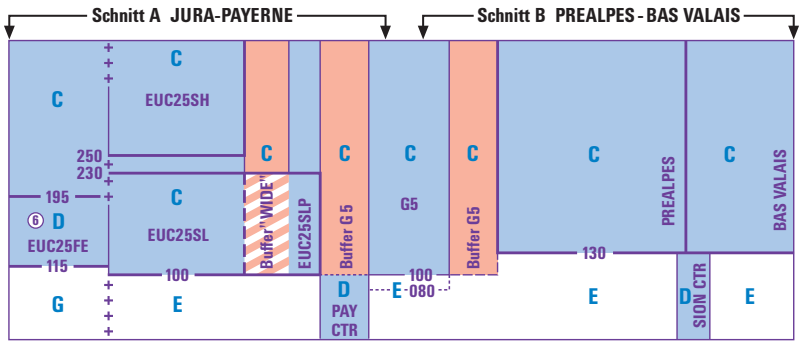

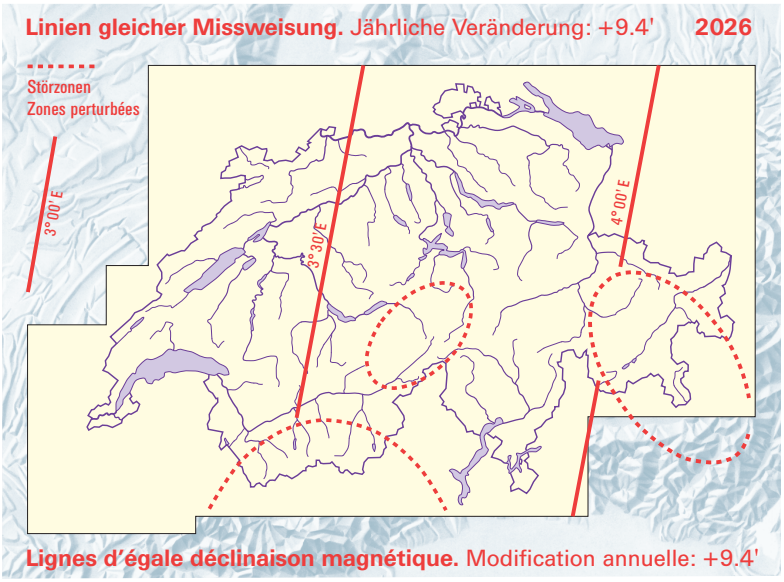

Name	ICAO	Service	FREQ
Alpnach	LSMA	TWR	128.475
		INFO	134.130
Ambri	LSPM	AD	118.530
Amlikon	LSPA	AD	120.130
Bad-Ragaz	LSZE	AD	123.505
Bâle-Mulhouse	LFSB	TWR	118.300
		ATIS	127.880
		INFO	130.900
Balzers HEL	LSXB	AD	119.805
Bellechasse	LSTB	AD	122.380
Bern-Belp	LSZB	TWR	121.030
		ATIS	125.130
		GLD	123.405
Bex	LSGB	AD	122.155
Biel-Kappelen	LSZP	AD	123.155
Birrfeld	LSZF	AD	123.555
		GLD	119.830
Bressaucourt	LSZQ	AD	122.055
Buochs	LSZC	TWR	119.625
		INFO	134.130
Buttwil	LSZU	AD	122.155
Courtelary	LSZJ	AD	124.605
Dittingen	LSPD	AD	118.180
Dübendorf	LSMD	TWR	118.975
Ecuvillens	LSGE	AD	120.630
Emmen	LSME	TWR	118.005
		INFO	134.130
Fricktal-Schupfart	LSZI	AD	119.555
Genève	LSGG	TWR	118.705
		ATIS	135.580
		INFO	126.350
Grenchen	LSZG	TWR/RMZ	120.105
		ATIS	121.105
		GLD	127.580
Gruyères	LSGT	AD	124.680
Hausen am Albis	LSZN	AD	130.755
Interlaken HEL	LSXI	AD	120.530
Kägiswil	LSPG	TWR/AD	128.475
		INFO	134.130
La Côte	LSGP	AD	123.655
Langenthal	LSPL	AD	119.405
Lausanne	LSGL	AD	123.205
		APCH INFO	118.830
Les Éplatures	LSGC	TWR	118.130
Locarno	LSZL	TWR/AD	134.825
		ATIS	133.455
		GLD	122.480
Lodrino	LSPR	AD	121.205
Lommis	LSZT	AD	119.305
Lugano	LSZA	TWR	120.250
		ATIS	121.175
Luzern-Beromünster	LSZO	AD	122.455
Meiringen	LSMM	TWR	130.155
		INFO	135.480
Mollis	LSZM	AD	134.830
Montricher	LSTR	AD	133.205
Môtiers	LSTO	AD	126.655
Münster	LSPU	AD	122.080
Neuchâtel	LSGN	AD	123.605
Olten	LSPO	AD	118.780
Payerne	LSMP	TWR	128.680
Raron	LSTA	AD	129.880
Reichenbach	LSGR	AD	127.705
Saanen	LSGK	AD	119.430
Samedan	LSZS	AFIS	135.330
		ATIS	136.160
Schaffhausen	LSPF	AD	121.055
Schänis	LSZX	AD	120.605
Schindellegi HEL	LSXS	AD	118.755
Sion	LSGS	TWR	118.275
		ATIS	130.630
		GLD	118.275
Sitterdorf	LSZV	AD	118.355
Speck-Fehraltorf	LSZK	AD	120.355
St. Gallen-Altenrhein	LSZR	TWR	135.430
		ATIS	123.780
St. Stephan	LSTS	AD	120.055
Thun	LSZW	AD	123.255
Triengen	LSPN	AD	124.530
Wangen-Lachen	LSPV	AD	123.205
Winterthur	LSPH	AD	134.980
Yverdon-les-Bains	LSGY	AD	131.130
Zermatt HEL	LSEZ	AD	130.005
Zurich	LSZH	TWR	118.100
		ATIS (VFR)	129.005
		INFO	124.700
Zweisimmen	LSTZ	AD	121.230

Höhenangabe, Indication d'altitude

FL 100	Höhenangabe Flight Level (FL), Indication d'altitude Flight Level (FL)
3000	Höhenangabe über Meer *(ft AMSL)*, Indication d'altitude *(ft AMSL)*
3000 AGL	Höhenangabe über Grund (ft AGL), Indication de la hauteur (ft AGL)

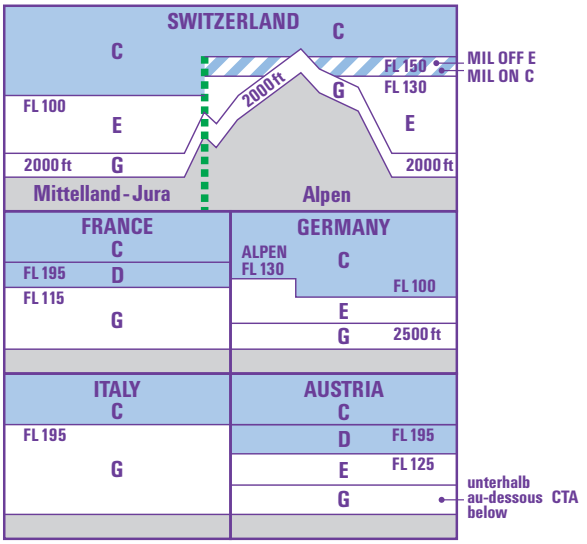

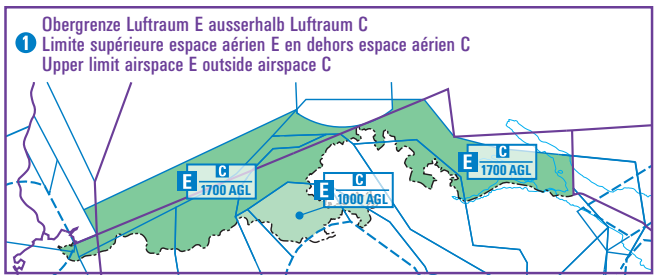

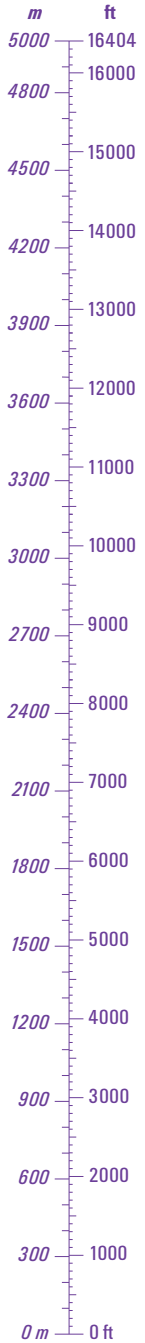

Kartenzeichen **Signes conventionnels**

FLUGPLÄTZE AÉRODROMES		Hartbelagpiste Piste revêtue	Unbefestigte Piste Piste non revêtue
dem öffentlichen Luftverkehr dienend destinés au trafic public			
Flugfelder (privat) Champs d'aviation (privés)			
Zivil- und Militär Civil et militaire mixte	ausser Betrieb hors service		keine vorhanden aucune disponible
Militär Militaire	ausser Betrieb hors service		keine vorhanden aucune disponible
Ausrichtung der längsten Piste Alignement de la piste la plus longue			
Hubschrauberflugplatz Héliport		Segelfluggelände Terrain de vol à voile	
Höhe in Fuss ü.M. Altitude en pieds		AERODROME *1411*	

C FL 660 / FL 195 — Generell für den Luftraum innerhalb der Schweiz
Valable pour l'espace aérien à l'intérieur de la Suisse

CTR Luftraum Klasse D — CTR
CTR Espace aérien classe

TMA Luftraum Klassen C D
TMA Espace aérien classes

TMA TEMPO D

TMA MIL TEMPO D — Zeitliche Benützung siehe: / Période d'utilisation voir: NOTAM

TMA Luftraum Klasse E
TMA Espace aérien classe

P, R, D — Sperr-, Flugbeschränkungs-, Gefahrengebiet NOTAM / MACRAS
Zone interdite, réglementée ou dangereuse

Gebiet mit vorgeschriebener Transponderschaltung TMZ
Zone avec transpondeur obligatoire

Gebiet mit Funkkommunikationspflicht RMZ G
Zone avec radio obligatoire

Fluginformationszone FIZ
Zone d'Information de Vol

Z 50
DVO
Mittelland -Jura / Alpen
Trennlinie
Ligne de séparation

FL 100 — Pufferzone zu AWY
Zone tampon
gilt ab dieser Höhe
valable dès cette altitiude

A9 / G5 — AWY

HX — Keine bestimmten Betriebszeiten
Pas d'heures précises de fonctionnement

Zu meidende Zone
Zone à éviter

Symbole für die Gefahrengebiete
Symboles pour zones dangereuses

Film- oder Fotoflüge
Vol photo

Luftkampf
Combat aérien

Erdangriffe ohne Munition
Attaques au sol sans munition

MIL — Erhöhte MIL-Fliegertätigkeit
Activité de vol militaire accrue

Fallschirm und Gleitschirmspringen
Saut avec parachute et paraplane

Segelflugzonen
Zones de vol à voile

Ballonfahrten
Ascensions en ballon

DR — Drohnenflüge
Vol d'engin téléguidé

Kunstflug (Akro)
Acrobatie

EKF — EKF-Einsätze
Engagement CGE

Erhöhte HELI-Fliegertätigkeit
Activité de vol helicoptère accrue

DCA — Ziel- und Schleppflüge für FLAB
Vol de pointage et de remorquage pour la DCA

Deltasegelflüge und Hängegleiter
Vol à voile avec deltaplane et parapente

Fesselballon
Ballon captif

MIL OFF	MIL ON
Ausserhalb Militärflugdienstzeiten **Hors des heures du service de vol militaire** **Outside of military operating hours**	**Militärflugdienstzeiten** **Heures du service de vol militaire** **Military operating hours** MON – FRI: 0730 – 1205 LT 1315 – 1705 LT **or NOTAM**

MIL-Nachtflüge JET/HEL/PROP
Vols de nuit MIL JET/HEL/PROP
JET/HEL/PROP MIL night flights

NOTAM (EXC: Air Policing and SAR Missions)

ZURICH TMA S1/S2/S3

HX

Information upon Airspace status:
BATMAN, MIL INFO V31, DUB TWR V01
resp. EMM TWR V02
LSZH TMA S1 HX: ZURICH TERMINAL 127.755MHz
LSZH TMA S2/S3 HX: ZURICH TERMINAL 127.755MHz

Untergrenzen TMA
Nördlich der Trennlinie Mittelland-Jura/Alpen gelten die auf der Karte angegebenen Untergrenzen oder 700 ft AGL, je nachdem welches die grössere Höhe ergibt.
Südlich der Trennlinie Mittelland-Jura/Alpen gelten die auf der Karte angegebenen Untergrenzen oder 1000 ft AGL, je nachdem welches die grössere Höhe ergibt.

Limites inférieures TMA
Au nord de la ligne de séparation Plateau-Jura/Alpes, les limites inférieures selon indication sur les cartes ou 700 ft AGL (valeur la plus elevée) sont applicables.
Au sud de la ligne de séparation Plateau-Jura/Alpes, les limites inférieures selon indication sur les cartes ou 1000 ft AGL (valeur la plus elevée) sont applicables.

Lower limits TMA
North of separation line Mittelland-Jura/Alps, lower limits as indicated on charts or 700 ft AGL whichever is higher are applicable.
South of separation line Mittelland-Jura/Alps, lower limits as indicated on charts or 1000 ft AGL whichever is higher are applicable.

Publisher: **Swiss Air Force**
Editor: **OMS**
Layout and Print: Federal Office of Topography swisstopo, CH-3084 Wabern

Basemap: Duplication and adaption of this Chart or parts of it in analog or digital form, in other purpose than private use, are only allowed with permission of Federal Office of Topography swisstopo.

Winkeltreue schiefachsige Zylinderprojektion
Navigation (GNSS): „WGS 84“

Projection conforme cylindrique à axe oblique
Navigation (GNSS): „WGS 84“

Nachführung der Basiskarte: 2025
Mise à jour de la carte de base: 2025

MIX
Paper | Supporting responsible forestry
FSC® C030149
www.fsc.org

© 2026
Bundesamt für Landestopografie swisstopo, 3084 Wabern
Office fédéral de topographie swisstopo, 3084 Wabern

Stand der Flugsicherungsangaben:
Renseignements aéronautiques à la date du: 2026 MAR 19

37. Ausgabe/37e édition

Gültig ab 19.03.2026
Valable à partir du 19.03.2026